NATIONS UNIES
MAURITANIE

Cadre de l'Action Anticipatoire : Sécheresse en Mauritanie

17 avril 2026

Barrage pour la rétention de l'eau à Hsey Sidi dans la région du Guidimakha. 2019. WFP/Maria Ludovica Carucci

Cadre de l'Action Anticipatoire
Sécheresse en Mauritanie

11 mars 2026 (Version Pilote développée par le Groupe de Travail Spécialisée en charge de l'Action Anticipatoire)

Approuvé par le CR le 02 avril 2026
Approuvé par le ERC le 17 avril 2026

Sommaire 2
Résumé exécutif 3
Executive summary 5
1. Introduction 7
Action anticipatoire – vision 7
Objectif du cadre 7
Principes de base 8
La sécheresse en Mauritanie 9
Chronologie de la crise 10
Cadre de coordination 11
2. Mécanisme de déclenchement 11
Prévisions 12
Déclencheurs 12
Suivi des prévisions et protocole d'activation 13
3. Plan d'action anticipatoire 14
Critères de sélection des activités 14
Activités par agence 16
Calendrier de mise en œuvre 19
Priorisation géographique 20
Ciblage des populations 22
4. Financements pré-arrangés 23
Le Fonds Central d'Intervention d'Urgence (CERF) 23
Co-financements 24
5. Apprentissage 25
Suivi et évaluation 25
Atelier de capitalisation 25
6. Dispositions finales 26
Annexe 1. Analyse historique des déclencheurs 27
Annexe 1. Composition du GTSAA 31

Résumé exécutif

La Mauritanie fait face à une vulnérabilité climatique structurelle, marquée par une exposition élevée et récurrente aux sécheresses, une variabilité pluviométrique accentuée, une dégradation des pâturages et une pression croissante sur des ressources hydriques déjà limitées. Dans un contexte où plus de 75 % du territoire est désertique et où les moyens de subsistance reposent largement sur l'agriculture pluviale et le pastoralisme, les déficits pluviométriques entraînent des effets rapides et profonds sur la sécurité alimentaire, la nutrition, l'accès à l'eau, les dynamiques de transhumance et la stabilité communautaire. Les analyses les plus récentes indiquent une aggravation des tendances, avec une hausse attendue de la fréquence et de l'intensité des sécheresses, tandis que 30 % de la population demeure en situation de vulnérabilité climatique extrême.

Face à ce risque croissant, un Groupe de Travail Spécialisé en charge de l'Action Anticipatoire (GTSAA) – regroupant les agences des Nations Unies, les services techniques nationaux et le Croissant-Rouge Mauritanien, sous la facilitation du DCAN et du BCR, avec l'appui technique de OCHA – a élaboré un cadre d'action anticipatoire pour mitiger l'impact humanitaire des sécheresses sur les populations les plus à risque dans la région du Guidimakha, en particulier dans les moughataas de Wompou, Selibaby et Ould Yengé, ayant le potentiel d'atteindre plus de 100 000 personnes avec un ensemble d'activités intégrées avant le début de la sécheresse. Ce cadre s'inscrit dans une dynamique nationale d'institutionnaliser l'action anticipatoire sous le leadership du DCAN, soutenue par les capacités renforcées de l'Office National de la Météorologie et par les initiatives existantes du PAM et du CRM.

Ce cadre repose sur les quatre piliers fondamentaux de l'action anticipatoire :

1. **Un mécanisme de déclenchement** fondé sur des données prévisionnelles et observationnelles, développé conjointement par l'ONM, l'Université de Columbia, OCHA/CDH et le GTSAA, afin de capter les événements de sécheresse sévère selon des seuils convenus à l'avance.
2. **Des activités anticipatoires** pré-arrangées, multisectorielles, conçues pour être mises en œuvre dans les fenêtres temporelles où elles maximisent leur impact.
3. **Un financement pré-arrangé**, comprenant un engagement de 2,5 millions USD du CERF, déboursé immédiatement dès l'activation d'un des deux déclencheurs non-cumulatifs.
4. **Un dispositif d'apprentissage**, comprenant suivi, évaluation, documentation inter-agences et revue après action (AAR), visant à améliorer la qualité, la rapidité, l'efficience et la dignité de la l'action anticipatoire.

Le cadre prévoit deux déclencheurs indépendants, correspondant à deux fenêtres d'opportunité :

1. **Déclencheur prévisionnel (fenêtre 1 – février à mai)** : on déclenche si les précipitations prévisionnelles de l'ONM de juillet-août-septembre à travers toute la Mauritanie sont dans les 45% des pires années de sécheresse, pour deux mois d'émission de prévisions consécutifs de février à mai inclus. L'activation enclenche un paquet complet d'activités couvrant la sécurité alimentaire, le WASH, la nutrition et l'engagement communautaire.
2. **Déclencheur observationnel (fenêtre 2 – août ou septembre)** : on déclenche si les précipitations observationnelles de CHIRPS cumulatives, moyenne à travers toute la Mauritanie, de la première décade de juillet à la décade actuelle inclus sont inférieures au seuil correspondant dans le tableau ci-dessous. Le déclenchement est validé conjointement par OCHA et l'ONM. Ce déclencheur active un second paquet d'activités ciblant prioritairement la préservation du cheptel, le soutien agricole, l'accès à l'eau, la nutrition et la sensibilisation.

Décade actuelle	*Seuil*
2ième juillet	6,6 mm
3ième juillet	13,6 mm
1ier août	22,6 mm
2ième août	31,9 mm
3ième août	41,7 mm

Les déclencheurs ne sont pas cumulatifs, ni dans les fenêtres, ni entre les fenêtres. C'est-à-dire qu'une fois qu'un seul déclencheur est atteint, le budget entier CERF est déboursé, et les déclenchements ultérieurs sont sans importance.

Le tableau ci-dessous montre les statistiques de base pour le mécanisme de déclenchement.

Statistiques du mécanisme de déclenchement

Statistiques par déclencheur *Années d'analyse : 2001-2025*

Déclencheur	*Période de retour*	*Probabilité d'activation*	*Années activées*
Prévisions	6,5 ans	15 %	2001, 2011, 2014, 2015
Observationnel	5,2 ans	19 %	2002, 2011, 2014, 2017, 2019

Statistiques globales

Période de retour globale	3,7 ans
Probabilité d'activation globale	27 %
Dépenses totales moyenne par année	0,8 M$

L'ERC a engagé jusqu'à 2,5 millions USD, ventilés entre les agences participantes (FAO, OIM, PAM, UNICEF). Une fois le cadre approuvé par le Coordonnateur Résident et l'ERC, et dès que l'un des deux déclencheurs est activé, 100 % du budget disponible est immédiatement décaissé selon le principe du « sans regret ». Si aucun déclencheur n'est atteint, les fonds restent disponibles pour la saison suivante, dans la limite de la validité du cadre.

Le présent cadre est valable pour une période initiale de deux ans suivant son approbation (2026-2027). La saison 2025 constituera une phase pilote, puisqu'elle représente la première expérience d'action anticipatoire interagences en Mauritanie. Pour 2027, les enseignements tirés du développement et de la mise en œuvre potentielle du cadre seront utilisés pour renforcer et étendre sa portée, en collaboration avec le GTSAA.

Executive summary

Mauritania faces structural climate vulnerability, marked by high and recurrent exposure to droughts, increased rainfall variability, pasture degradation, and growing pressure on already limited water resources. In a context where more than 75% of the territory is desert and where livelihoods rely heavily on rainfed agriculture and pastoralism, rainfall deficits rapidly trigger severe impacts on food security, nutrition, water access, transhumance dynamics, and community stability. The most recent analyses indicate a worsening trend, with an expected rise in the frequency and intensity of droughts, while 30% of the population remains in a situation of extreme climate vulnerability.

In response to this growing risk, a Specialized Working Group on Anticipatory Action (GTSAA) – bringing together UN agencies, national technical services, and the Mauritanian Red Crescent, under the facilitation of the DCAN and the Resident Coordinator's Office, with technical support from OCHA – has developed an anticipatory action framework to mitigate the humanitarian impact of drought on the most at-risk populations in the Guidimakha region, particularly in the moughataas of Wompou, Selibaby and Ould Yengé, with the potential of reach more than 100 000 people through a set of integrated activities before the onset of the drought. This framework aligns with a national effort to institutionalize anticipatory action under the leadership of the DCAN, supported by strengthened capacities of the National Meteorological Office and existing initiatives led by WFP and the Mauritanian Red Crescent.

This framework is built on the four fundamental pillars of anticipatory action:

1. **A triggering mechanism based on forecast and observational data**, jointly developed by ONM, Columbia University, OCHA/CHD, and the GTSAA, designed to detect severe drought events according to pre-agreed thresholds.
2. **Pre-agreed, multisectoral anticipatory activities**, designed to be implemented within time windows where they can maximize their impact.
3. **Pre-arranged financing**, including a USD 2.5 million commitment from CERF, disbursed immediately upon activation of one of the two non-cumulative triggers.
4. **A learning system**, including monitoring, evaluation, inter-agency documentation and an After-Action Review (AAR), aimed at improving the quality, speed, efficiency and dignity of anticipatory action.

The framework includes two independent triggers, corresponding to two windows of opportunity:

1. **Forecast-based trigger (Window 1 – February to May):** triggered if the ONM's forecast rainfall for July-August-September across Mauritania is within the 45% worst drought years, for two consecutive issue months of forecasts from February to May inclusive. The activation launches a full package of activities covering food security, WASH, nutrition, and community engagement.
2. **Observation-based trigger (Window 2 – August or September):** triggered if the cumulative CHIRPS observational rainfall, averaged across Mauritania, from the first ten days of July to the current ten days inclusive, is below the corresponding threshold in the table below. Triggering is validated jointly by OCHA and ONM. This trigger activates a second package of activities focusing primarily on livestock protection, agricultural support, water access, nutrition, and awareness-raising.

Current dekad	*Threshold*
2nd July	6.6 mm
3rd July	13.6 mm
1st August	22.6 mm
2nd August	31.9 mm
3rd August	41.7 mm

Triggers are not cumulative, either within windows or between windows. This means that once a single trigger is reached, the entire CERF budget is disbursed, and subsequent triggers are irrelevant.

The table below shows the basic statistics for the trigger mechanism.

Trigger Mechanism Statistics

Stats by trigger *Analysis years: 2001-2025*

Trigger	*Return period*	*Activation probability*	*Years activated*
Forecast	6.5 years	15%	2001, 2011, 2014, 2015
Observational	5.2 years	19%	2002, 2011, 2014, 2017, 2019

Overall stats

Overall return period	3.7 years
Overall probability of activation	27%
Average total spending per year	$0.8M

The ERC has committed up to USD 2.5 million, allocated across participating agencies (FAO, IOM, WFP, UNICEF). Once the framework is approved by the Resident Coordinator and the ERC, and as soon as one of the triggers is activated, 100% of the funds are immediately disbursed following the “no regret” principle. If no trigger is activated, the funds remain available for the following season, within the validity period of the framework.

The present framework is valid for an initial period of two years following its approval (2026–2027). The 2026 season will serve as a pilot phase, as it represents the first inter-agency anticipatory action experience in Mauritania. For 2027, lessons learned from both the development and the potential implementation of the framework will be used to strengthen and expand its scope, in collaboration with the GTSAA.

1. Introduction

Action anticipatoire – vision

Il existe un large accord au sein du secteur humanitaire international sur la nécessité de passer d'une approche réactive à une approche proactive, qui conduirait à une réponse plus efficace et digne tout en protégeant les gains de développement durement acquis.

L'action anticipatoire est définie comme une intervention mise en œuvre avant un événement dangereux prédit, afin de prévenir ou de réduire ses impacts sur les vies humaines, les moyens de subsistance et les besoins humanitaires, avant qu'ils ne se manifestent pleinement. Ce mécanisme fonctionne de manière optimale lorsque les activités, ainsi que les déclencheurs ou règles de prise de décision, sont convenus à l'avance, et que des décisions sont prises pour garantir le décaissement rapide de financements préalablement alloués.[1]

Aujourd'hui, nous pouvons prévoir l'occurrence et l'impact humanitaire de certains chocs climatiques et météorologiques avec une certitude croissante. En tirant parti des différentes approches analytiques, les événements météorologiques inhabituels peuvent non seulement être prédits, mais leurs impacts projetés peuvent être atténués de manière proactive sur la base d'actions anticipatoire pré-identifiées.

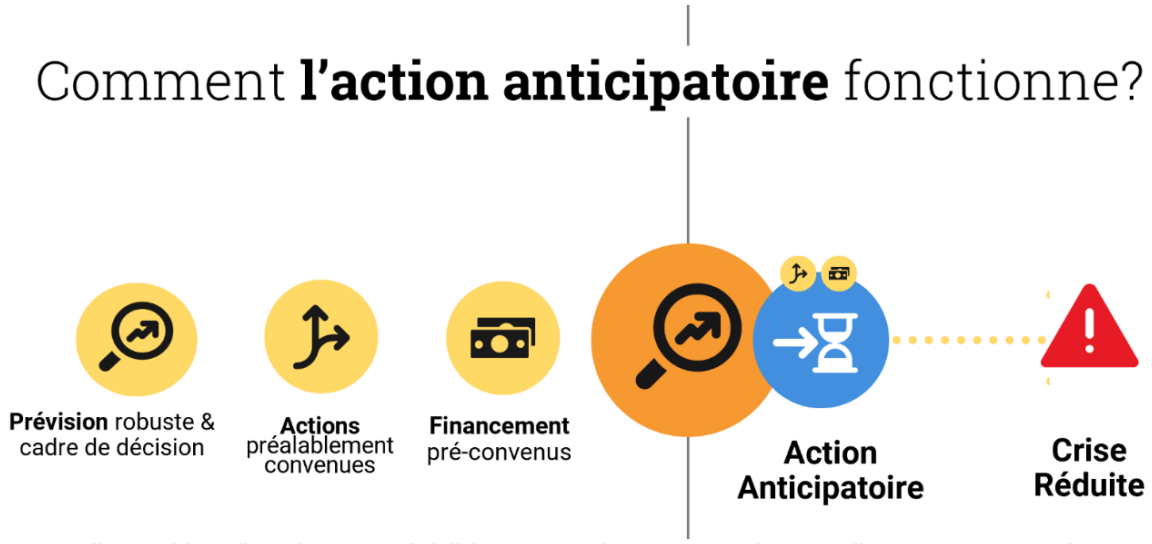

Agir avant l'apparition d'un danger prévisible permet donc non seulement d'apporter une assistance plus valorisante aux populations affectées, mais c'est également nettement plus efficace (coût moindre) que la réponse humanitaire traditionnelle.

Objectif du cadre

L'objectif de ce cadre est de démontrer comment l'action anticipatoire collective réduit l'impact humanitaire de la sécheresse sur les personnes les plus vulnérables dans la région du Guidimakha en Mauritanie, spécifiquement les moughataas de Wompou, Selibaby et Ould Yengé, durant les saisons 2026 et 2027. Dès que le seuil de déclenchement est atteint, les paquets d'activités seront mis en œuvre par les agences des Nations Unies et leurs partenaires, y compris le Gouvernement, pour subvenir aux besoins de la population à risque avant que l'impact humanitaire du choc ne se fasse ressentir.

[1] Grand Bargain Caucus on Scaling Up Anticipatory Action, 2024. *Outcome document, commitments*.

Ce cadre combine les trois composantes clés de l'action anticipatoire, tous convenus au préalable :

- Un modèle de prévision et des déclencheurs convenus à l'avance, intégrés dans un processus décisionnel clair (**prévision et déclencheurs**).
- Des activités pré-arrangées qui peuvent mitiger l'impact de la sécheresse sur les communautés vulnérables (**actions anticipatoires**).
- Un financement préétabli, comprenant un engagement du CERF pour le financement des mesures d'urgence par le biais de modèles CERF préremplis (**financement**).

Une approche collaborative convenue à l'avance pour documenter les preuves des réalisations du cadre (**apprentissage**) est également pré-convenue. L'action anticipatoire reste un espace innovant, nécessitant une « preuve par l'action ».

En d'autres termes, ce cadre établit quand et sur quelle base l'action sera déclenchée pour un événement spécifique ; quel montant de financement ira à quelle agence des Nations Unies ; et pour quelles activités, dans un temps prédéfini, le financement sera utilisé. Enfin, le cadre comprend des éléments convenus à l'avance sur l'apprentissage à partir des activités réalisées.

Principes de base

En adéquation avec les autres cadres collectifs facilités par OCHA, ce cadre d'action anticipatoire a suivi les préalables ci-dessous :

- ***Consensus, simple, rapide et prévisible*** : Le cadre est le résultat d'un travail consensuel d'un groupe de partenaires désireux et capables de mener des actions anticipatoires et qui disposent déjà d'une expertise avérée en matière d'actions anticipatoires. Les experts membres du groupe ayant développé ce document proviennent du PAM, FAO, UNICEF, OIM, OMS, le Dispositif National de Prévention et de Réponse aux Crises Alimentaires et Nutritionnelles (DCAN), l'Office National de la Météorologie (ONM), La Délégation Générale à la Sécurité Civile et à la Gestion des Crises (DGSCGC), le Registre Social (Programme de Taazour), avec l'appui du Bureau du Coordinateur Résident (BCR) du système des Nations Unies et du Bureau de la Coordination des Affaires Humanitaires (OCHA). Toutes les étapes pour arriver au cadre anticipatoire ont été franchies de manière consensuelle.
- ***Donner la priorité à une approche multisectorielle*** *:* un accent important a été mis sur l'approche multisectorielle. Les activités à mettre en œuvre couvriront les secteurs de la sécurité alimentaire et moyens d'existence ; l'eau, l'assainissement et l'hygiène (EAH) ; et la nutrition. Un volet multisectoriel a également été inclus sous la forme d'engagement communautaire, essentiel pour la diffusion de messages d'alertes précoces et la sensibilisation des populations à risque.
- ***Support à la localisation*** *:* les agences retenues pour ce cadre vont assurer la mise en œuvre du projet par des organisations internationales, mais également des organisations locales afin de renforcer les capacités de ces dernières.
- ***Utilisation de transferts monétaires dans la mesure du possible*** *:* afin de contribuer au maintien de l'économie locale, le transfert monétaire a été retenu comme modalité prioritaire d'intervention pour les activités de distribution – dans les contextes opérationnels qui le permettent et dans les communes où cette modalité est applicable.
- ***Capturer l'apprentissage*** *:* des activités de suivi, d'évaluation et d'apprentissage seront documentées tout au long de la mise en œuvre du cadre. Les résultats seront présentés à l'Équipe de Réponse d'Urgence (ERT – *Emergency Response Team*) afin de voir comment les activités d'action anticipatoire pourraient être intégrées dans l'assistance humanitaire, mais également dans le Nexus, y compris le cycle de gestion des risques de catastrophe.

- ***Assurer la centralité de la protection :*** la protection sera assurée chaque agence dans le cadre de la mise en œuvre de leurs activités de façon centrale – c'est-à-dire intégrer à toute étape et dimension de leur projet.
- ***Promouvoir la redevabilité envers les populations affectées :*** la redevabilité envers les populations affectées est aussi importante pour l'action anticipatoire que n'importe quelle intervention humanitaire et demeure prioritaire parmi les considérations des agences, tant de façon conjointe qu'indépendante. La ligne verte du gouvernement sera utilisée comme approche unique, promue à travers l'engagement communautaire de l'OIM, tandis que chaque agence mettra en place son mécanisme de feedback et de plainte.

La sécheresse en Mauritanie

Pays sahélien d'Afrique de l'Ouest comptant 4,9 millions d'habitants, la Mauritanie est confrontée à une vulnérabilité climatique structurelle, principalement liée à la sécheresse. Avec plus de 75 % de son territoire désertique, ses écosystèmes arides et semi-arides subissent une pression croissante due à l'irrégularité des précipitations, à la hausse des températures et à la désertification. Située à l'orée du Sahara, l'équilibre entre la population et son environnement est fragilisé par les effets du changement climatique et l'intensification des chocs qu'il engendre[2].

En outre, La Mauritanie figure parmi les pays les plus vulnérables au changement climatique à l'échelle mondiale. Selon le RISK INFORM Index 2025, elle est classée 4e sur 194 pays pour le risque de sécheresse, avec un score de 9 sur 10 et près de 30 % de la population en situation de « vulnérabilité climatique extrême »[3]. Plus de 22 % de la population n'a pas accès à une source d'eau potable de base[4], situation aggravée par la dégradation des ressources hydriques. D'après ThinkHazard!, un épisode de sécheresse est attendu en moyenne tous les cinq ans[5]. Les régions méridionales, notamment le Guidimakha, l'Assaba et le Hodh El Chargui, sont particulièrement exposées[6].

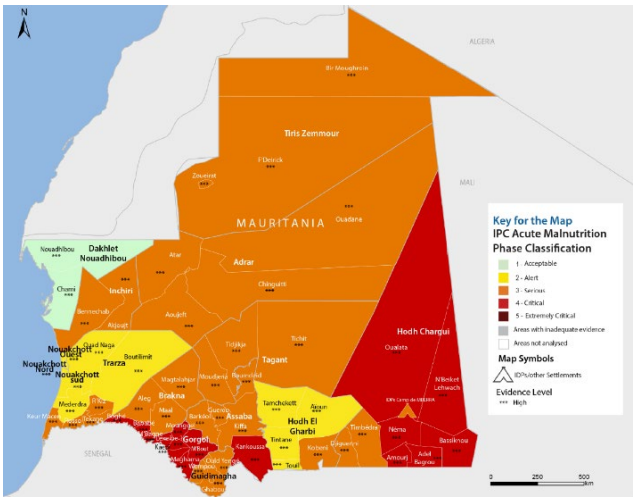

Figure.7.Vue.d"ensemble.de.la.situation.actuelle.IPC.(novembre.868❶_février.868❷¡.Fewsnet¡

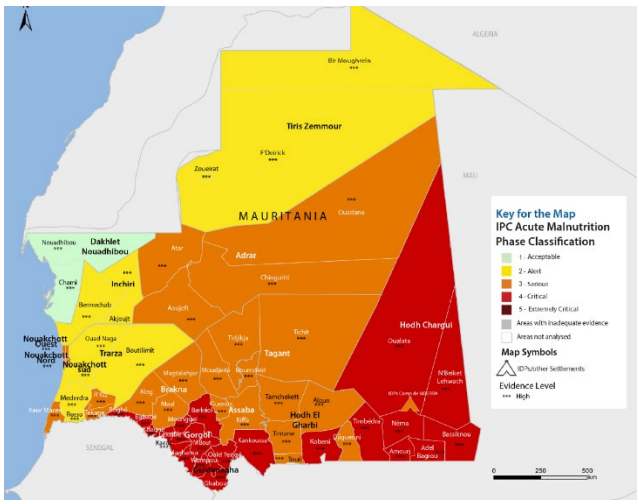

Figure.8.Vue.d"ensemble.de.la.situation.projetée.IPC.(juin_octobre.868❷¡.Fewsnet¡

[2] IOM, "Guidamakha's Village Committees Lead Resilience Efforts in Mauritania"
[3] Notre Dame Global Alliance Initiative (ND-GAIN), "Rank countries by ND-GAIN Country Index, Vulnerability and Readiness"
[4] UNICEF, « Mauritanie : La soif d'une vie meilleure »
[5] Think Hazard, Mauritanie
[6] ReliefWeb, "Mauritania - Droughts : 2022"

Historiquement, la Mauritanie a connu plusieurs sécheresses sévères, notamment dans les années 1970[7] et 1980, entraînant une désertification accrue et des impacts socio-économiques majeurs. Selon le FMI, les anomalies climatiques devraient s'intensifier, avec une hausse des températures et une fréquence accrue des vagues de chaleur, ainsi qu'un déficit pluviométrique par rapport à la moyenne historique[8].

Les épisodes récurrents de sécheresse entraînent une dégradation des pâturages et une baisse de la disponibilité en eau, affectant directement les moyens de subsistance et aggravant l'insécurité alimentaire. Selon l'analyse IPC de la malnutrition aiguë pour la période novembre 2025-octobre 2026, près de 179 000 enfants âgés de 6 à 59 mois souffrent ou risquent de souffrir de malnutrition aiguë, dont plus de 42 000 en malnutrition aiguë sévère (SAM)[9]. Environ 71 000 femmes enceintes ou allaitantes sont également concernées. La situation nutritionnelle est influencée par la sécheresse, les mauvaises conditions d'eau, assainissement et hygiène, les épidémies de maladies infectieuses et les pratiques alimentaires insuffisantes. Durant la période de pointe (juin-octobre 2026), jusqu'à 22 Moughataas devraient être en Phase 4 (Critique) et 31 en Phase 3 (Sérieuse), incluant le camp de réfugiés de Mberra[10].

En Mauritanie, le changement climatique devrait accentuer la fréquence et l'intensité des sécheresses, aggravant l'érosion des sols, la désertification, les vagues de chaleur et la variabilité des précipitations. Conformément aux analyses du GIEC, ces évolutions affectent de manière disproportionnée les zones arides et sahéliennes, où l'exposition élevée et la dépendance aux ressources naturelles amplifient les risques pour les moyens de subsistance et la sécurité humaine. L'anticipation de ces risques, à travers la planification fondée sur les données climatiques, la mise en place de systèmes d'alerte précoce et d'un cadre d'action anticipatoire contribue au renforcement de capacités d'adaptation des communautés et des infrastructures, capacité essentielle afin de réduire les impacts humanitaires et environnementaux à court et long terme[11].

Chronologie de la crise

La dynamique annuelle de la crise climatique en Mauritanie est marquée par une succession de phases agro-pastorales étroitement dépendantes des pluies, qui conditionnent à la fois la disponibilité des pâturages et la sécurité alimentaire des ménages. La sécheresse récurrente intensifie la soudure pastorale et agricole, prolongeant les déficits alimentaires et accentuant la pression sur les ressources naturelles.

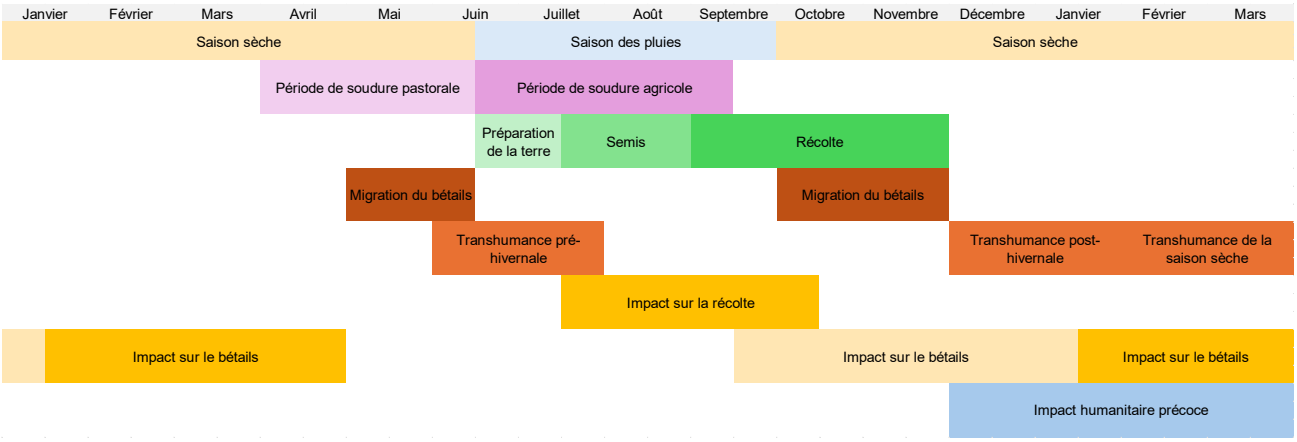

[7] UNW-DPC, "Drought conditions and management strategies in Mauritania", 2014
[8] FMI, Islamic Republic of Mauritania: Selected Issues, 3 février 2023
[9] IPC, Mauritania: IPC Acute Malnutrition Snapshot | November 2025 - October 2026 (Published on 5 January, 2026), 5 janvier 2026
[10] Ibid
[11] Anticipation Hub, « Profil de la Mauritanie »

Face à la dégradation des pâturages, les migrations de bétail et les cycles de transhumance pré- et post-hivernale deviennent plus précoces, plus longues et plus risquées, exposant les troupeaux à une baisse de l'état corporel, une hausse de la mortalité et des tensions accrues autour des points d'eau et des zones de parcours. Ces perturbations saisonnières, exacerbées par l'irrégularité des pluies et les chocs climatiques, se traduisent par des impacts croissants sur la production agricole, les moyens d'existence pastoraux et les besoins humanitaires précoces, soulignant la nécessité d'un déclenchement rapide et fondé sur l'anticipation pour atténuer les effets de la sécheresse.

L'établissement de cette chronologie est essentiel car il permet de comprendre quand les impacts d'un déficit pluviométrique commenceront à se matérialiser, d'identifier les points de bascule entre stress environnemental et crise humanitaire, et de déterminer précisément le moment opportun pour activer les interventions AA.

Cadre de coordination

Un groupe de travail composé du PAM, FAO, UNICEF, OIM, OMS, le Croissant-Rouge Mauritanien (CRM), le Dispositif National de Prévention et de Réponse aux Crises Alimentaires et Nutritionnelles (DCAN), l'Office National de la Météorologie (ONM), La Délégation Générale à la Sécurité Civile et à la Gestion des Crises (DGSCGC), le Registre Social (Programme de Taazour) et le Bureau du Coordinateur Résident (BCR) du système des Nations Unies, avec le soutien technique de OCHA, a mené le travail d'élaboration du cadre AA pour la sécheresse en Mauritanie. Capitalisant sur l'existant mis en place durant l'élaboration du plan AA du PAM, ce groupe a également bénéficié de l'intérêt injecté dans l'action anticipatoire en Mauritanie après la 1e Plateforme de Dialogue Régionale sur l'Action Anticipatoire en Afrique de l'Ouest et du Centre. En effet, le DCAN, qui préside actuellement les activités de l'AA, a pour objectif d'institutionnaliser le travail à travers la création d'un Groupe de Travail Spécialisé en charge de l'Action Anticipatoire (GTSAA), validée par décret gouvernementale. De plus, le projet mené actuellement par le PAM (2024-2028), en collaboration avec IRI et AGRHYMET, notamment pour renforcer les capacités de l'ONM dans la production de prévisions et l'élaboration de mécanisme de déclenchement, marque un tournant dans la manière d'assurer la pérennité de l'AA au niveau national et a permis à ce cadre d'avoir un mécanisme de déclenchement porté par une instance gouvernementale.

Ce cadre est une version pilote, construit sur les plans AA existants, à savoir le Plan Action Anticipatoire (PAA) du PAM et le Protocole d'Action Précoce (PAP) du CRM. A travers la création du GTSAA et les compétences accrues de l'ONM, le document a pour objectif d'être mis à l'échelle nationale, couvrant d'autres zones géographiques, d'autres aléas, et d'autres secteurs, tout en assurant une collaboration grandissante entre les acteurs œuvrant dans la gestion des risques de catastrophes en Mauritanie.

2. Mécanisme de déclenchement

Les membres du GTSAA impliqués dans l'élaboration de ce cadre, avec l'expertise de l'ONM, le National Center for Disaster Preparedness (NCDP, anciennement IRI) de l'Université de Columbia et le Centre de données humanitaires (CDH) de OCHA, ont développé le mécanisme de déclenchement visant à capturer des évènements graves de sécheresse en Mauritanie. Ce mécanisme comprend deux déclencheurs : le déclencheur prévisionnel, basé sur les saisonnières produites de l'ONM, et le déclencheur observationnel, basé sur les précipitations observées de CHIRPS. Il vise à capturer les événements de sécheresse avec une sévérité qui se produit en moyenne 1 fois sur 4 ans.

Prévisions

Les sources de données utilisées pour le mécanisme de déclenchement de l'AA doivent être performantes sur plusieurs critères. Il s'agit notamment de la capacité de prévision, du délai de prévision, de la fréquence de publication, de l'accès public et de la disponibilité des données historiques. Lorsque les sources de données nationales et internationales sont aussi performantes les unes que les autres sur ces critères, les sources nationales doivent être privilégiées.

L'ONM a développé avec le NCDP un système de prévisions saisonnières calibré spécifiquement pour la Mauritanie. En tant que tel, il devrait être plus précis pour la Mauritanie que les modèles globaux. Ces prévisions sont affichées dans le Maproom de NCDP pour la Mauritanie.

Déclencheurs

Les déclencheurs sont définis comme suit :

1. ***Déclencheur prévisionnel (fenêtre 1)*** : on déclenche si les précipitations prévisionnelles de l'ONM de juillet-août-septembre à travers toute la Mauritanie sont dans les 45 % des pires années de sécheresse[12], pour deux mois d'émission de prévisions consécutifs de février à mai inclus.
2. ***Déclencheur observationnel (fenêtre 2)*** : on déclenche si les précipitations observationnelles de CHIRPS[13] cumulatives, moyenne à travers toute la Mauritanie, de la première décade de juillet à la décade actuelle inclus sont inférieures au seuil correspondant dans le tableau ci-dessous :

Décade actuelle	***Seuil***
2ième juillet	6,6 mm
3ième juillet	13,6 mm
1ier août	22,6 mm
2ième août	31,9 mm
3ième août	41,7 mm

Les déclencheurs ne sont pas cumulatifs, ni dans les fenêtres, ni entre les fenêtres. C'est-à-dire qu'une fois qu'un seul déclencheur est atteint, le budget entier CERF est déboursé, et les déclenchements ultérieurs sont sans importance.

Le calendrier approximatif des déclenchements possibles est montré dans le tableau ci-dessous :

Fenêtre	***Déclencheur***	***Date approx. de déclenchement***
1 (prévisionnel)	Prévisions de février et mars	Fin mars
	Prévisions de mars et avril	Fin avril
	Prévisions d'avril et mai	Fin mai
2 (observationnel)	2ième ou 3ième décade juillet	Mi-août
	1ier, 2ième, ou 3ième décade août	Mi-septembre

[12] Comme défini dans le Maproom de NCDP avec le « Frequency of trigger events » réglé sur 45% et la version des prévisions « JAS fcst v8 ».
Le Maproom est disponible à https://iridl.ldeo.columbia.edu/fbfmaproom2/mauritania
[13] Spécifiquement l'ensemble de données publié sur HDX ici : https://data.humdata.org/dataset/mrt-rainfall-subnational, utilisant seulement les données de « version » « final ».

Le tableau ci-dessous montre les statistiques[14] historiques du mécanisme de déclenchement[15].

Statistiques du mécanisme de déclenchement

Statistiques par déclencheur *Années d'analyse : 2001-2025*

Déclencheur	*Période de retour*	*Probabilité d'activation*	*Années activées*
Prévisions	6,5 ans	15 %	2001, 2011, 2014, 2015
Observationnel	5,2 ans	19 %	2002, 2011, 2014, 2017, 2019

Statistiques globales

Période de retour globale	3,7 ans
Probabilité d'activation globale	27 %
Dépenses totales moyenne par année	0,8 M$

Mesures d'exactitude *Années d'analyse : 2001-2025*

Déclencheur	*Exactitude*	*Taux de détection*	*Taux de fausse alarme*	*Précision*	*Score F1*
Prévisions	80 %	44 %	0 %	100 %	62 %
Observationnel	84 %	56 %	0 %	100 %	71 %
Globale	92 %	78 %	0 %	100 %	88 %

Suivi des prévisions et protocole d'activation

Le protocole d'activation a pour objectif de clairement identifier le processus à exécuter une fois que les seuils de déclenchement sont atteints, et est ainsi crucial à préétablir. Le protocole comprend 3 étapes clés : (1) la validation des données, (2) la validation de l'activation, et (3) la phase d'exécution (mise en œuvre et communication). Dans ce cadre pilote d'action anticipatoire pour la sécheresse, deux scénarios doivent être envisagés (indiqués par la flèche noire dans l'infographie ci-dessous), à savoir :

- En cas d'activation basée sur les prévisions (atteinte des seuils de déclenchement sur deux mois consécutifs entre février et mai), l'information initiale émanera de l'ONM. Elle sera validée en collaboration avec IRI et OCHA, avant d'être envoyée à l'ensemble du GTSAA – cela correspond à l'étape 1 (validation des données) – le tout sous 24 heures. L'étape 2 (validation de l'activation) prend effet lorsque le DCAN aura convoqué le GTSAA en réunion de consultation dès réception des informations de l'ONM, également sous 24 heures. A la suite de cette consultation, l'étape 3 (exécution) pourra démarrer, avec une communication de DCAN, en tant que lead du GTSAA, au

[14] Les mesures sont décrites ici : https://fr.wikipedia.org/wiki/Matrice_de_confusion (le « taux de détection » correspond au « rappel », tandis que le « taux de fausse alarme » est le nombre de faux positifs divisé par le nombre de négatifs réels). Un « positif » est considéré d'être une des 9 pires années dans la période d'analyse (le rang 12 ou pire), basé sur les données de « Humanitarian Bad Years » compilées par le NCDP.

[15] Il est à noter que les déclenchements historiques des prévisions dans ce tableau ne concordent pas avec les déclenchements historiques affichés dans le Maproom (indiqué par un fond jaune). Cela est dû à une différence des méthodes pour déterminer les déclenchements historiques. Néanmoins, un déclenchement de l'année actuelle dans le Maproom reste exact pour le déclencheur de ce cadre car les méthodes se concordent seulement pour l'année actuelle.

gouvernement, au bureau de la Coordonnatrice Résidente, au CERF pour le décaissement des fonds et à ROWCA pour la communication publique.

- En cas d'activation basée sur les observations (cumul de pluie entre juillet et août), l'information initiale émanera de OCHA. Elle sera validée en collaboration avec l'ONM avant d'être envoyée à l'ensemble du GTSAA – cela correspond à l'étape 1 (validation des données) – le tout sous 24 heures. L'étape 2 (validation de l'activation) prend effet lorsque le DCAN aura convoqué le GTSAA en réunion de consultation dès réception des informations de OCHA, également sous 24 heures. A la suite de cette consultation, l'étape 3 (exécution) pourra démarrer, avec une communication du DCAN, en tant que lead du GTSAA, au gouvernement, au bureau de la Coordonnatrice Résidente, au CERF pour le décaissement des fonds et à ROWCA pour la communication publique.

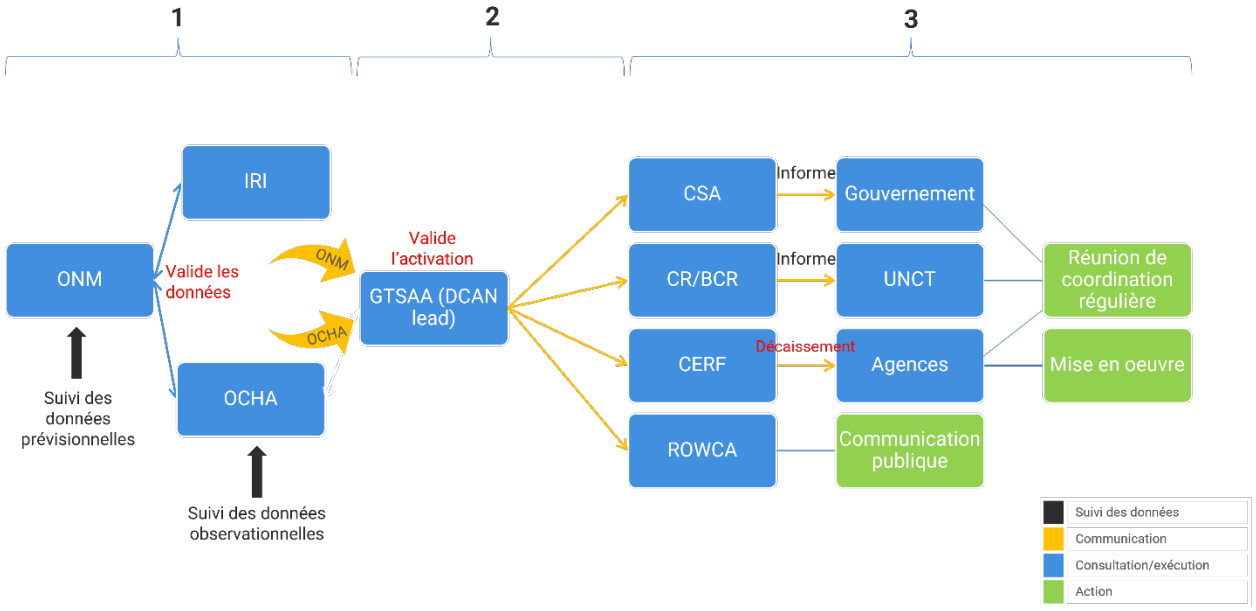

Il est important de noter que durant la période de suivi, février-mai pour le déclencheur prévisionnel, et juillet-août pour le déclencheur observationnel, une communication sera toujours faite, que le seuil soit atteint ou non, pour éviter toute confusion des parties prenantes. Cette communication se fera de la même façon que précédemment décrit, à savoir l'ONM communique sur le déclencheur prévisionnel et OCHA communique sur le déclencheur observationnel. Des mails seront prérédigés pour chaque cas de figure afin d'éviter tout retard susceptible de se produire.

3. Plan d'action anticipatoire

Critères de sélection des activités

Les actions anticipatoires visent à interrompre la gravité d'un choc – dans ce cas l'impact de la sécheresse – sur les ménages vulnérables en ciblant les populations les plus à risque. Le ciblage de l'action anticipatoire ("à risque") est donc distinct et différent du ciblage de la réponse humanitaire qui est déterminé par les besoins existants ("dans le besoin").

Les critères suivants ont été appliqués pour sélectionner les actions :

- ***Caractère anticipatoire*** *:* L'action est-elle efficace pour prévenir ou réduire l'impact humanitaire avant qu'un choc produise des besoins humanitaires ? Comment une agence peut-elle mesurer le succès de ces actions anticipées ?
- ***Capacité à livrer dans la fenêtre d'opportunité*** *:* Est-il possible de réaliser l'action efficacement avec le délai prévisionnel disponible, c'est-à-dire dans la fenêtre d'opportunité ? Quel est le dernier moment de déclenchement pour la réalisation d'activités concrètes, prenant en compte leurs temps de préparation ?
- ***Capacité opérationnelle*** *:* L'agence et ses partenaires d'implémentation ont-ils la capacité institutionnelle (ressources thématiques, logistiques, administratives, financières, humaines) pour mettre en œuvre l'action efficacement compte tenu du délai et de l'échelle ?
- ***Approche sans regret*** : En cas de fausse alerte, les actions proposées seront-elles bénéfiques aux populations plutôt que de les affecter négativement ?
- ***Bénéfice d'une approche multisectoriel*** *:* Est-ce qu'il y a des actions par d'autres agences nécessaires pour que vos actions puissent atteindre un succès maximal ?
- ***Effet multiplicateur*** *:* Bien que les actions anticipatoires soient des actions humanitaires, y a-t-il des bénéfices attendus qui peuvent contribuer à protéger les progrès acquis de développement ou avoir d'autres avantages ?

Activités par agence

Le tableau ci-dessous reprend les activités par secteur et par agence, y compris le nombre de personnes ciblées et les budgets. Les détails de chaque projet d'agence sont repris dans les fiches de projet tels que renseignés dans OneGMS.

Objectif du Cadre AA : Réduire l'impact de la sécheresse annoncée sur les individus et les communautés vulnérables et à risque dans les moughataas de Wompou, Selibaby et Ould Yengé dans la région du Guidimakha, par une action anticipatoire collective et intersectorielle.					
Secteur	Agence	Budget CERF (US$)*	Personnes ciblées**	Fenêtre***	Activités anticipatoires
Sécurité alimentaire *Protéger et promouvoir la sécurité alimentaire et les moyens de subsistance contre le risque de sécheresse*	FAO	500 000	12 100	1	• Distribution d'intrants agricoles adaptés à la sécheresse (*prioritaire*) • Distribution de kits maraîchers (semences, outils, encadrement & suivi technique) pour la saison sèche (*prioritaire*) • Actions pour la gestion de l'eau à utilisation agricole/pastorale (sensibilisation, installation et réhabilitation d'ouvrages, distribution des réservoirs de stockage etc.) (*prioritaire*) • Promotion des techniques de conservation de fourrages (*prioritaire*) • Transfert monétaire (cash+ ; besoins alimentaires) (*prioritaire*) • Distribution de kits maraîchers (semences, outils, encadrement & suivi technique) pour la saison froide (*secondaire*) • Vaccination et déparasitage du cheptel (*secondaire*) • Distribution d'aliment de bétail (*secondaire*) • Atelier de consultation • Atelier de capitalisation
			11 500	2	• Distribution de kits maraîchers (semences, outils, encadrement & suivi technique) pour la saison froide • Transfert monétaire adaptés au contexte au réalités socio-économiques • Vaccination et déparasitage du cheptel • Distribution d'aliments bétail • Sensibilisation pour le déstockage de bétail • Atelier de consultation • Atelier de capitalisation
	PAM	950 000	34 449	1	• Transfert monétaire inconditionnel pour couvrir les besoins alimentaires et autres besoins tels que les semences adaptées à la sécheresse, les intrants pour les cultures de contre saison ou les aliments bétail
Nutrition *Atténuer la mortalité liée à la malnutrition aiguë grâce à une*			15 942	2	• Transfert monétaire en top aux activités du secteur nutrition
	UNICEF	400 000	36 624	1	• Renforcement de la surveillance nutritionnelle à travers la capacitation de tous les mère/gardiens d'enfants sur le suivi de leur état nutritionnel avec PB (périmètre brachial) mère, et le recours précoce aux soins si nécessaire (*prioritaire*)

détection précoce et des soins de qualité					• Appui à la sensibilisation des communautés pour un renforcement des pratiques favorables d'Alimentation du Nourrisson et du Jeune Enfant (ANJE), de nutrition maternelle et des autres pratiques familiales essentielles pour la prévention de la malnutrition (*prioritaire*) • Supplémentation en Multi micronutriments (MNP) des enfants de 6-23 mois, en vitamine A des enfants de 6-59 mois et le déparasitage des enfants de 12-59 mois (*secondaire*) • Mise en place d'un stock tampon d'Aliments Thérapeutiques Prêts à l'Emploi (ATPE) et de laits thérapeutiques pour prévenir les ruptures de stock et renforcer le traitement de la MAS (*secondaire*)
				2	• Renforcement de la surveillance nutritionnelle à travers la capacitation de tous les mère/gardiens d'enfants sur le suivi de leur état nutritionnel avec PB (périmètre brachial) mère, et le recours précoce aux soins si nécessaire • Appui à la sensibilisation des communautés pour un renforcement des pratiques favorables d'Alimentation du Nourrisson et du Jeune Enfant (ANJE), de nutrition maternelle et des autres pratiques familiales essentielles pour la prévention de la malnutrition • Supplémentation en Multi micronutriments (MNP) des enfants de 6-23 mois, en vitamine A des enfants de 6-59 mois et le déparasitage des enfants de 12-59 mois • Mise en place d'un stock tampon d'Aliments Thérapeutiques Prêts à l'Emploi (ATPE) et de laits thérapeutiques pour prévenir les ruptures de stock et renforcer le traitement de la MAS
WASH *Garantir l'accès à l'eau pour la consommation face au risque de sécheresse, y compris la promotion de l'hygiène*	UNICEF	400 000	54 480	1	• Fourniture, stockage et traitement d'urgence de l'eau potable pour les communautés affectées (*prioritaire*) • Réhabilitation/renforcement de points d'eau existants (*prioritaire*) • Distribution de kits d'hygiène, et fournitures de réapprovisionnement (*secondaire*) • Promotion des bonnes pratiques d'hygiène (gestion de la chaine de l'eau, TED (Technical Evaluation Document), gestion des excrétas) (*secondaire*)
				2	• Distribution de kits d'hygiène, et fournitures de réapprovisionnement • Promotion des bonnes pratiques d'hygiène (gestion de la chaine de l'eau, TED (Technical Evaluation Document), gestion des excrétas)
Multisectoriel *Permettre aux communautés une prise de décision informée*	OIM	250 000	108 900	1 ou 2	• Dissémination de messages d'alerte conjointes (canaux numériques, médias et relais locaux, équipes mobiles) • Sensibilisation communautaire (réunions villageoises, porte-à-porte, relais des comités locaux)

Budget : Les agences bénéficient du même budget, que ça soit la fenêtre 1 ou la fenêtre 2, étant donné que le décaissement sera à 100% dès qu'une activation est confirmée – c'est-à-dire, il n'y a pas de ventilation budgétaire entre fenêtre.*

*Cibles** : Pour les agences (UNICEF, OIM) qui prévoient les mêmes activités pour chaque fenêtre, la cible est la même ; pour les agences (PAM, FAO) qui ont différentes activités prévues, la cible varie.*

*Fenêtres*** : chaque fenêtre opère indépendamment en fonction du mécanisme de déclenchement. C'est-à-dire, si le seuil prévisionnel est atteint, le paquet d'activité de la fenêtre 1 sera mis en œuvre ; si le seuil observationnel est atteint, le paquet d'activité de la fenêtre de 2 sera mis en œuvre. Les activités de la fenêtre 1 sont marquées comme prioritaire et secondaire pour déterminer quand elles seront mises en œuvre vis-à-vis de la chronologie de la crise. Ce point est repris sous forme d'illustration dans la section suivante « Calendrier de mise en œuvre » et de façon détaillée dans le plan de travail « workplan » des projets des agences.*

Harmonisation des activités

- *Messages d'alerte précoce* : d'un commun accord, l'activité de diffusion des messages d'alerte précoce sera conduite sous le lead de l'ONM, à travers le PAA du PAM. Le contenu de ce premier message a été élaboré conjointement avec les agences pour capter la dimension multisectorielle du risque et les mesures d'atténuations. Dans un deuxième temps, l'OIM assurera le relai de messages sectoriels pour l'ensemble des agences à travers ses activités d'engagement communautaire. Cette approche a été décidée sur la base d'une volonté d'assurer une communication harmonisée ainsi que d'optimiser les fonds pour d'autres activités.
- *Transferts monétaires* : le PAM et la FAO ont prévu des activités de transferts monétaires pour sauvegarder les moyens d'existence des bénéficiaires et amoindrir le risque d'insécurité alimentaire causé par une sécheresse et donc une soudure précoce. Toujours dans une optique d'assurer une harmonisation des interventions, les deux agences se sont accordées sur une même valeur de transfert, basée sur la méthodologie du PAM. Celle-ci prend en compte les recommandations gouvernementales suivantes :

Montant	Scénario de panier total (n= nombre de personnes dans le ménage)
Besoins alimentaires des ménages : 500 MRU par personne et par mois	- *n*500 MRU + 2 000 MRU, si le ménages est agriculteur* - *n*500 MRU + 1200 MRU, si le ménage est éleveur* - *n*500 MRU + 2 000 MRU + 1200 MRU, si le ménage est agriculteur et éleveur*
Ménages **agricoles** : 12kg de Sorgho (8kg pour le semis et 4 pour le re-semis) au prix de 140 MRU et 2kg de Niébé au prix de 160 MRU, soit 2 000 MRU au total	
Ménages **pastoraux** : Aliment bétail 1000 MRU + 200 MRU intrants vétérinaires, soit 1 200 MRU au total	

Calendrier de mise en œuvre

Sur la base de la chronologie de la crise agro-pastorale, les fenêtres d'opportunité ont été identifiées afin d'aligner le déclenchement des activités AA avec la séquence réelle d'apparition des impacts liés à la sécheresse. Ce processus repose sur l'analyse croisée des indicateurs saisonniers (début de la soudure, calendrier cultural, migration du bétail, disponibilité en eau) et des seuils de déclenchement, permettant d'ordonner les interventions selon leur efficacité temporelle. Regroupés autour de deux moments d'opportunité de déclenchement **non-cumulatif** (mars, avril ou mai pour le déclencheur prévisionnel et août ou septembre pour le déclencheur observationnel), les paquets d'activités ont pour objectif de fournir l'assistance la plus critique pour mitiger l'impact de la sécheresse.

Le premier paquet d'activités intervient suite à l'atteinte des seuils de deux mois consécutifs durant la période de suivi (février-mai), soit au mois de mars, avril ou mai, basé sur les données prévisionnelles, pour maximiser les faibles pluies prévues et optimiser les récoltes, comprenant l'engagement communautaire à travers la diffusion de messages d'alertes précoces et la conduite de campagne de sensibilisation, l'assistance aux besoins alimentaires et agricoles, l'accès à l'eau et la prévention de la malnutrition aigüe. Des activités sont aussi prévues pour une mise en œuvre en fin de saison des pluies, focalisées sur la survie du cheptel et l'impact humanitaire d'une soudure précoce.

Le deuxième paquet d'activité intervient sur la base des données observationnelles en fin de saison, soit en août ou septembre, afin de préserver le cheptel et anticiper l'impact humanitaire d'une soudure précoce sur les populations les plus vulnérables. Ces activités comprennent également la conduite de campagne de sensibilisation et la diffusion de messages d'alerte, en plus d'une assistance agricole pour préserver le bétail et permettre des activités de maraichage, de l'assistance nutritionnelle, particulièrement chez les enfants, et des activités assainissement pour prévenir des flambées épidémiques.

Les illustrations ci-dessous reprennent les deux paquets d'activités dans la chronologie de la crise, aligné sur les déclencheurs.

<u>Paquet 1</u> (déclenchement prévisionnel en février **et** mars, **ou** en mars **et** avril, **ou** en avril **et** mai) :

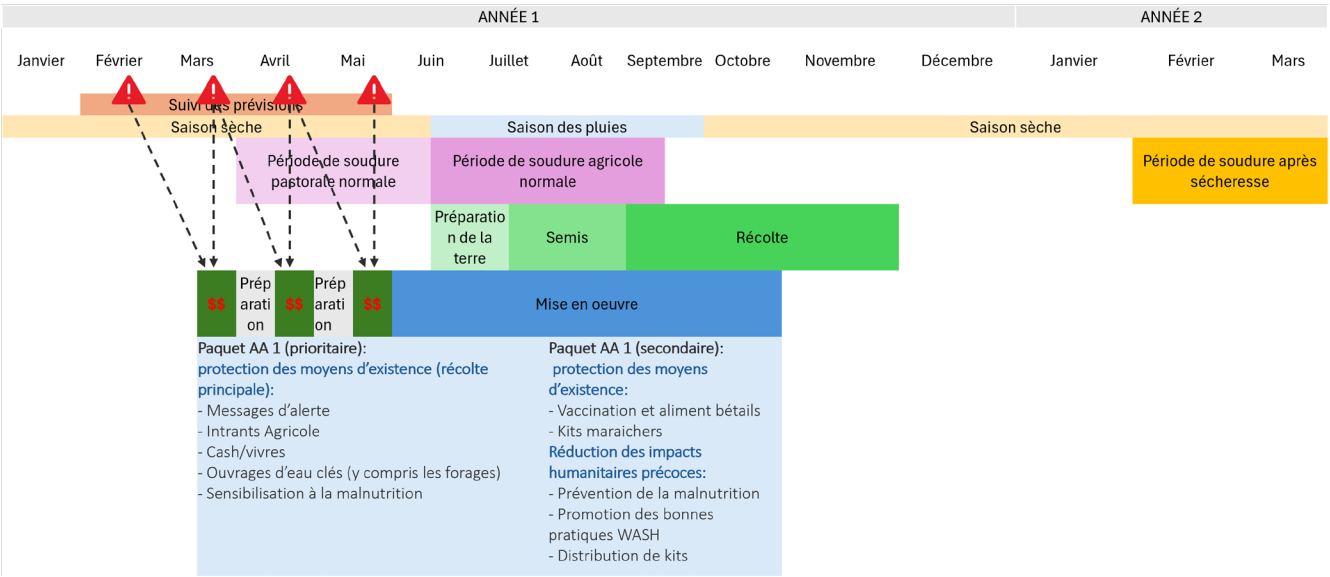

Paquet 2 (déclenchement observationnel, en août **ou** septembre) :

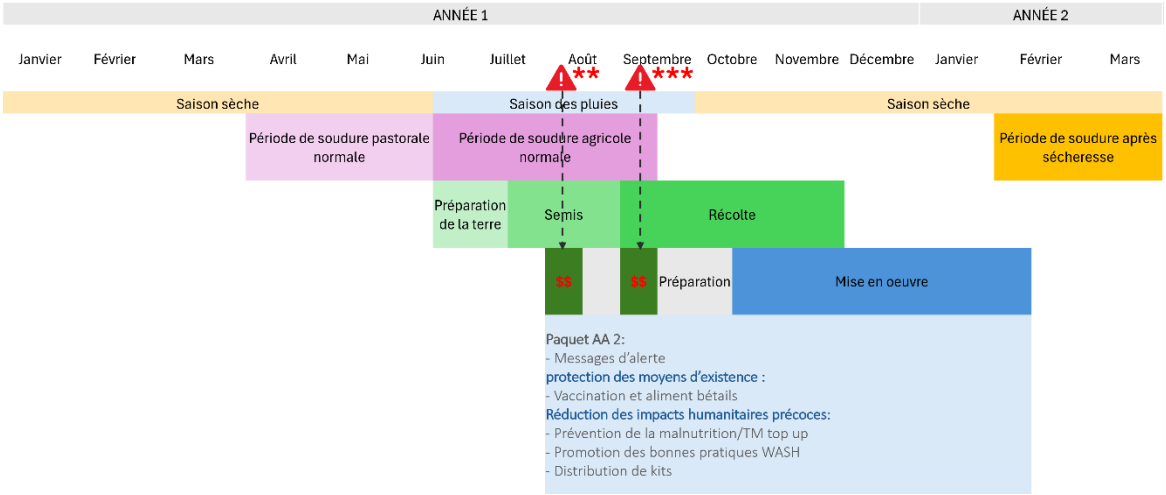

Priorisation géographique

La priorisation géographique de ce cadre d'action anticipatoire suit un processus à 4 étapes :

1. *Identification de la région prioritaire*

La région du Guidimakha a été priorisée pour mener des actions anticipatoires collectives contre la sécheresse pour mitiger l'impact humanitaire, sur la base de facteurs climatiques, socio-économiques et stratégiques :

- Située dans la zone sahélienne du sud du pays, elle est particulièrement vulnérable à la variabilité pluviométrique et aux déficits hydriques récurrents, caractéristiques d'un climat où les saisons des pluies sont courtes, irrégulières et de plus en plus instables sous l'effet du changement climatique. Les projections nationales confirment par ailleurs une intensification attendue des périodes sèches et des extrêmes climatiques dans les décennies à venir, augmentant le risque de sécheresse agricole prolongée.
- Cette fragilité climatique affecte directement une économie reposant largement sur l'agriculture pluviale, le pastoralisme et l'exploitation des ressources naturelles, rendant les ménages fortement dépendants de la disponibilité en eau et particulièrement exposés en cas de déficit pluviométrique. La pression croissante sur les terres cultivables, les pâturages et les points d'eau amplifie également les tensions entre communautés agricoles, éleveurs et groupes transhumants dans le Guidimakha, ce qui réduit la capacité d'adaptation locale et aggrave la vulnérabilité socio-économique.
- Sur le plan stratégique, le Guidimakha constitue la principale région agricole du pays et toute perturbation pluviométrique y entraîne des répercussions disproportionnées sur la production vivrière, les marchés locaux et la stabilité des moyens d'existence ; de plus, la région figure parmi les zones prioritaires identifiées dans les initiatives mauritaniennes d'action anticipatoire dédiées aux risques de sécheresse, notamment dans le protocole d'alerte précoce (PAP) du Croissant-Rouge Mauritanien (CRM) et le Plan d'Action Anticipatoire (PAA) du PAM[16].

[16] Les zones d'intervention sélectionnées dans le PAA du PAM inclus le Guidimakha et l'Assaba et dans le PAP du CRM inclus le Guidimakha, Brakna, Gorgol et Assaba.

2. *Alignement avec les initiatives en cours*

La sélection de la région du Guidimakha s'aligne sur la priorisation géographique du CRM et du PAM pour leurs initiatives AA. Au-delà du niveau Administratif 2 (le Guidimakha), et à travers un consensus du groupe d'élaboration du cadre, l'alignement géographique s'est également fait au niveau Administratif 3 en sélectionnant les moughataas de Wompou, Selibaby et Ould Yengé, basé sur les critères de ciblage du PAM pour la mise en œuvre des activités dans le PAA sécheresse (repris ci-dessous). Cette harmonisation permet de maximiser les interventions anticipatoires prévues, tout en évitant les doublons d'activités.

Critères de ciblage géographique du PAM pour la mise en œuvre des activités prévues dans le PAA sécheresse :

Récurrence d'insécurité alimentaire aiguë (PopP_ph3à5 du Cadre Harmonisé)

Récurrence des sécheresses sur 30 ans (1981- 2015)

Accessibilité en termes d'infrastructures de transport, de réseaux de communication et de disponibilité des services de base

Zones des moyens d'existence (zone agropastorale et culture pluviale)

Récurrence de malnutrition 2018 à 2024 10- 15% et plus

Peuplement de la localité (afin d'avoir un impact substantiel en cas d'intervention)

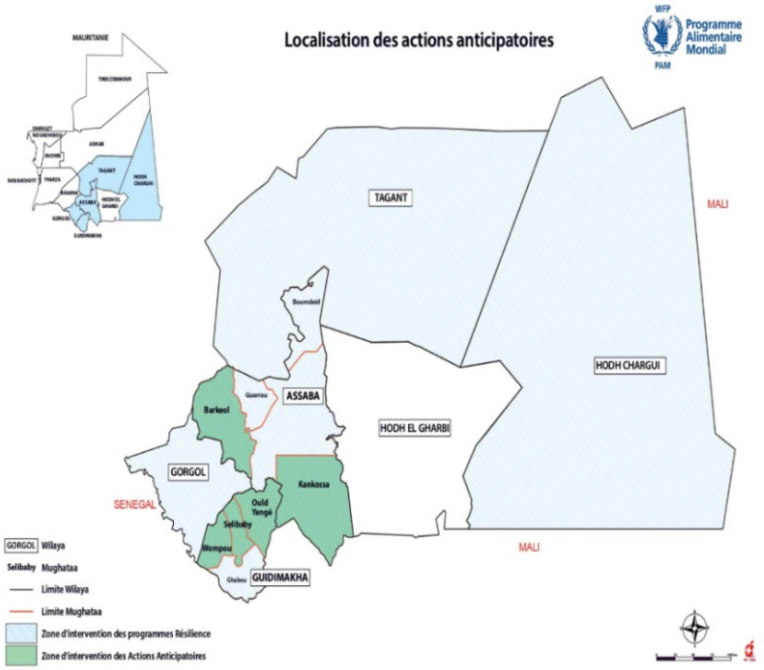

3. *Ciblage géographique pré-activation*

La méthodologie harmonisée des CODEP (Comissions départementales), qui répertorient les communes par scoring en fonction de plusieurs indicateurs (y compris l'insécurité alimentaire et malnutrition), a été identifiée comme outil pour définir les zones d'interventions au niveau administratif 4 (communes). Une réunion sera organisée pré-activation pour exploiter les dernières données disponibles et relever les communes les plus vulnérables pour l'exécution des activités.

4. *Ciblage géographique post-activation*

Dans le cas où les seuils d'activation seraient atteints, les agences et partenaires s'engagent à se coordonner sur la sélection des communes d'intervention dans les 3 moughataas pré-identifiés, afin d'assurer un paquet d'assistance complémentaire et intégré. L'identification des communes vulnérables en phase 3 sera présentée lors d'un atelier de consultation (prévu parmi les activités de la FAO de ce cadre), organisé avec les autorités locales de la région du Guidimakha, pour valider les données et garantir que les zones prioritaires reflètent la réalité du contexte.

Lors de la finalisation de ce cadre, un exercice de simulation sur table sera conduit pré-activation pour (1) garantir la disponibilité des informations nécessaires afin d'identifier les zones d'intervention, (2) assurer que toutes les parties prenantes sont identifiées et que les canaux de communication soient mis en place,

et (3) clarifier les aspects d'ordre logistique afin de garantir qu'en cas d'activation, l'atelier sera organisé dans les plus brefs délais.

Ciblage des populations

Le ciblage des populations a été fait sur la base d'une approche conjointe, afin d'assurer la mise en œuvre de paquets multisectoriels intégrés. L'objectif est de garantir que les communautés les plus vulnérables puissent bénéficier de la même assistance pour minimiser l'impact de la sécheresse sur leurs moyens de subsistance et qualité de vie, y compris l'accès aux services EAH et en matière de nutrition.

Le processus prend comme point de départ les critères de ciblage du Groupe de Soudure du gouvernement, fournis par le Registre Social (Programme de Taazour). Les catégories de critères sont : occupation principale, biens de consommation/équipements non-productifs, type de logement, nombre d'adultes actifs dans le ménage, taille maximale des ménage et possession de bétail. Sur cette base, chaque agence prend en compte les critères sectoriels spécifiques, repris dans le tableau ci-dessous :

Secteur	Critère de ciblage	Nombre de personnes ciblées
Engagement communautaire/ Multisectoriel	- Ménages ayant faible accès à l'information : enclavement, barrière linguistique, absence radio/téléphone - Communautés présentant des risques élevés de tensions ou de mauvaise circulation de l'information – Groupes vulnérables : cheffes de ménage, personnes handicapées, transhumants souvent non enregistrés	108 900
Sécurité alimentaire et agriculture	– Ménages ayant comme activité principale une activité dépendant de la pluviométrie (agriculture pluviale et / ou pastorale), – Propriétaire ou locataire d'une terre agricole d'au moins 0,5ha – Possession d'au moins 05 petits ruminants et 01 gros ruminants. – Nombre d'adultes actifs dans le ménage : compte tenu de la nécessité d'avoir des membres actifs dans le ménage pour les activités agricoles et pastorales, ne pas exclure les ménages ayant des membres actifs supérieur à 2 car c'est plutôt un atout – Ne pas exclure les ménages dont la taille est supérieure à 21 personnes pour les mêmes raisons ci-dessus, – Ne pas exclure les ménages ayant un logement dont le nombre de pièces est supérieur à 2 (dans les zones ciblées la plupart des ménages vivent dans la même concession avec des logements dont le nombre de pièces dépasse habituellement 2 et ceci pour favoriser la cohésion sociale) – Gestion des cas spéciaux, notamment l'inclusion des foyers pastoraux très mobiles non enregistrés dans le RS, via un enrôlement défini et validé par les communes et les services techniques compétents	46 549
WASH	- Enfants (U5), femmes enceintes et allaitantes, personnes âgées et personnes vivant avec handicap - Ménages en situation d'extrême pauvreté avant la sécheresse - Santé publique et risques de maladies hydriques ; incidence de la malnutrition aigüe sévère et modérée - Déficit d'accès aux services WASH de base	54 480
Nutrition	- Enfants (U5) - Prévalence de la malnutrition issue de la SMART de 2025 dans chacune des régions affectées - Incidence de la malnutrition aigüe sévère et modérée	36 624

Dispositions additionnelles :

- Les listes de populations fournies par le **Registre Social** serviront de base pour toutes les agences. Celles-ci seront sollicitées si le seuil d'activation est atteint, en fournissant les localités d'intervention (identifiées communément avec le GTSAA et après consultation avec les autorités locales) et les critères de sélection.
- La FAO et le PAM s'assureront qu'il n'y ait pas de doublons entre leur liste de bénéficiaires, particulièrement en ce qui concernent les activités de transferts monétaires, pour éviter que différents ménages reçoivent différents montants, étant donné que les transferts monétaires seront équivalent à 100% du panier minimum, et que la valeur de transfert a été harmonisé entre les deux agences et n'est donc pas complémentaire.
- Le ciblage pour les activités de l'OIM devra prendre en compte l'intégralité des bénéficiaires identifiées par les autres agences pour assurer que toute personne recevant une assistance ait été informé à travers les activités d'engagement communautaire.
- Des questions pour l'étude rapide de baseline seront incluses lors du ciblage, pour assurer un point de comparaison avec les résultats des PDM.

4. Financements pré-arrangés

Le Fonds Central d'Intervention d'Urgence (CERF)

Pour ce cadre d'action anticipatoire pour la sécheresse en Mauritanie, le Coordonnateur des secours d'urgence (ERC) a engagé jusqu'à 2.5 millions de dollars du CERF en cas d'une activation complète du cadre d'action anticipatoire contre la sécheresse. Tous les fonds seront décaissés via le guichet de réponse rapide du CERF.

Le CERF décaisse les fonds une fois que trois conditions sont remplies :

- Approbation par le Coordonnateur Résident du Cadre d'Action Anticipatoire de la Mauritanie et du dossier de candidature du CERF comprenant un chapeau de candidature, des propositions de projets et des budgets spécifiques à chaque agence ; et
- Approbation par l'ERC du cadre d'action anticipatoire de la Mauritanie et du dossier de candidature du CERF comprenant un chapeau de candidature, des propositions de projets spécifiques à l'agence et des budgets spécifiques à l'agence (cela peut être une approbation pré-convenue) ; et
- Activation du déclencheur préalablement convenu, dans un délai maximum de deux ans à compter de l'approbation du cadre par l'ERC.

La proposition de la ventilation budgétaire est comme suit :

Agence	Secteur	Budget (USD)
PAM	Sécurité alimentaire (fenêtre 1) / Nutrition (fenêtre 2)	950 000
FAO	Sécurité alimentaire (agriculture)	500 000
UNICEF	WASH	400 000
	Nutrition	400 000
OIM	Multisectoriel (engagement communautaire)	250 000
Total		**2 500 000**

Le CERF débloquera les fonds selon le principe de "sans regret" dès que le déclencheur correspondant sera atteint (voir section 2). Lorsqu'un déclencheur est activé, le CERF enverra des lettres d'approbation aux agences concernées, puis procédera au décaissement de l'ensemble des fonds pour la fenêtre

correspondante. Les fenêtres d'opportunités opèrent de façon indépendante ; il ne peut pas y avoir une accumulation des déclencheurs. C'est-à-dire, si le déclencheur basé sur les prévisions atteint le seuil d'activation, le paquet d'activité prévue pour la fenêtre 1 sera mis en œuvre. Si ce seuil n'est pas atteint, le suivi de la saison se poursuit avec le déclencheur basé sur les données observationnelles. Dans le cas où le seuil de ce déclencheur est atteint, les activités prévues pour la fenêtre 2 seront mis en œuvre. Cela implique que le budget total sera décaissé en une fois, si le seuil de l'un ou l'autre déclencheur est atteint. Si aucune des deux fenêtres n'est déclenchée, les fonds restent pré-arrangés pour l'année suivante (jusqu'à la fin de la période de validité de deux ans du cadre).

Les scénarios de décaissement sont repris dans le tableau ci-dessous :

Scenario	Déclenchement	Secteurs d'activités prévues	Budget (non cumulatif)
Scenario 1 (Fenêtre 1)	Atteinte des seuils de déclenchement de deux mois consécutifs entre février et mai	Sécurité alimentaire, WASH, Nutrition, Multisectoriel (engagement communautaire)	2 500 000
Scenario 2 (Fenêtre 2)	Atteinte du seuil de déclenchement en août **ou** septembre	Sécurité alimentaire (agriculture), WASH, Nutrition, Multisectoriel (engagement communautaire)	2 500 000

Des informations additionnelles sont disponibles dans les documents de projet du CERF et les communications du CERF. Toute modification des projets et des budgets doit être approuvée par le Secrétariat du CERF, conformément à la pratique habituelle.

Le fait de disposer d'un cadre d'action anticipatoire soutenu par le CERF n'exclut pas (ni ne garantit) l'octroi de financements supplémentaires du CERF au titre de la Réponse Rapide pour un pays en cas d'une urgence humanitaire sévère, que ce soit pour le même choc ou pour d'autres.

Co-financements

Ce cadre a été développé sur la base des initiatives existantes, à savoir le PAA du PAM et le PAP du CRM. Le PAA du PAM adopte le même mécanisme de déclenchement qui est prévu dans ce cadre, et permettra ainsi un co-financement de leurs activités. Le financement reçu à travers ce cadre, en cas d'activation, servira ainsi de top-up pour les activités prévues dans le PAA, aligné sur le paquet conjoint de ce cadre. Le PAP du CRM adopte un autre mécanisme de déclenchement, avec un seuil plus modéré et l'utilisation d'autres sources de données météorologiques, bien que des discussions sont en cours pour harmoniser les mécanismes.

Ce cadre est un pilote inter-agence et servira pour la mobilisation de ressources auprès d'autres parties prenantes (i.e. bailleurs traditionnels, instituts financiers internationaux, service d'assurance) pour une mise à l'échelle nationale.

5. Apprentissage

L'action anticipatoire collective demeure un domaine innovant. À ce titre, les cadres collectifs facilités par OCHA accordent une importance particulière à la production de preuves et à l'apprentissage, chacun étant appuyé par un plan clair de suivi, d'évaluation et de capitalisation. Chaque cadre est analysé afin de déterminer si : 1) l'action humanitaire anticipatoire collective à grande échelle fonctionne et déclenche effectivement une réponse ; 2) cette réponse est plus rapide ; 3) plus efficace, notamment en termes de coûts ; et 4) plus digne pour les populations concernées.

Les éléments prévus pour identifier les leçons apprises de manière assidue sont repris ci-dessous.

Suivi et évaluation

Le dispositif de suivi et évaluation accompagne la mise en œuvre du cadre d'action anticipatoire afin d'assurer une coordination fluide, de mesurer la performance collective et de documenter les apprentissages.

Des **réunions de coordination régulières** permettront de suivre l'avancement des activités, d'identifier les difficultés opérationnelles et d'harmoniser les approches entre agences. Celles-ci seront convoquées par le DCAN, entité gouvernementale en charge de l'action anticipatoire au Mauritanie, en collaboration avec le BCR et l'appui technique de OCHA. Une **fiche de suivi** sera également élaborée dans ce sens afin de documenter les progrès de la mise en œuvre.

Une **visite terrain conjointe**, menée par le DCAN et le BCR, sera aussi organisée afin de témoigner de la mise en œuvre des projets et de leur impact sur la population. Cette mission sera l'occasion d'organiser des consultations en groupe avec les bénéficiaires ; elle permettra également de documenter les histoires d'impact et assurer la cohérence entre les fiches de projet, la réalité terrain et l'opérationnalité de la coordination.

Chaque organisation conduira en fin de mise en œuvre son propre suivi **post-distribution (PDM)** à l'aide d'un questionnaire harmonisé (élaboré conjointement pré-activation), intégrant des indicateurs spécifiques à l'anticipation, tels que la rapidité, l'adéquation de la réponse et la perception des ménages sur le caractère anticipatoire de l'assistance reçue. Les agences s'engagent à partager les données issues des différents PDM qui seront ensuite consolidées pour produire une analyse inter-agences, offrant une vision commune des performances du cadre. Dans la mesure du possible, des questions pour mener une étude rapide de **baseline** seront incluses lors du ciblage des populations pour capter le niveau socio-économique des populations et leur état de préparation, afin que les résultats du PDM puissent être comparables.

Enfin, les agences s'engagent aux modalités du CERF de soumettre le **rapportage intermédiaire et final** selon les délais indiqués dans OneGMS.

Atelier de capitalisation

L'atelier de capitalisation (inscrit comme activité de la FAO dans ce cadre) constitue un moment clé de l'apprentissage collectif. Il inclut la conduite d'une **revue après action** (AAR), permettant d'analyser de manière structurée la chronologie des décisions, la pertinence du déclenchement, le fonctionnement de la coordination et la qualité globale de la réponse anticipatoire.

En plus de l'AAR, l'atelier offre un espace de réflexion plus large sur l'ensemble du dispositif national d'action anticipatoire, y compris le fonctionnement des mécanismes de suivi, les capacités institutionnelles et les perspectives de mise à l'échelle. Les conclusions issues de cet exercice alimentent une synthèse stratégique destinée à renforcer l'efficacité, la rapidité et la dignité des futures activations.

6. Dispositions finales

Les agences s'engagent à coordonner, sous la facilitation du DCAN et du BCR, avec l'appui technique d'OCHA, l'élaboration des messages clés liés au cadre, y compris durant les phases d'élaboration, d'activation et de retour d'expérience.

En cas d'activation du cadre, une coordination étroite menée par le DCAN, avec l'appui du BCR et de OCHA, permettra au minimum la publication d'un communiqué de presse conjoint ainsi que la mutualisation et l'amplification des contenus diffusés sur les réseaux sociaux.

Afin de renforcer la cohérence du message et le plaidoyer en faveur de l'action anticipatoire, les agences s'engagent à mettre à disposition l'ensemble des ressources visuelles (photos, vidéos) ainsi que les histoires d'impact, dès qu'elles seront disponibles.

Le présent cadre est valable pour une période initiale d'environ deux ans suivant son approbation par l'ERC (2026-2027). La saison 2026 constituera une phase pilote, puisqu'il s'agira de la première expérience d'action anticipatoire interagences en Mauritanie. Lors de la saison 2027, les enseignements tirés du développement et de la mise en œuvre potentielle du cadre seront appliqués afin de renforcer et d'élargir sa portée, en collaboration avec le groupe d'action anticipatoire.

Annexe 1 : analyses historiques[17] du déclencheur

Mécanisme de déclenchement globale

Le tableau ci-dessous montre les déclenchements historiques comparé aux « mauvaises années » (les « Humanitarian Bad Years ») compilées par NCDP, et les allocations CERF historiques.

Année	Déclenche prévisions	Déclenche observations	Classement de mauvaises années	Montant allocation CERF (USD)
2025	False	False		0
2024	False	False	30	0
2023	False	False	30	0
2022	False	False	30	0
2021	False	False	10	0
2020	False	False	16	0
2019	False	True	8	0
2018	False	False	30	0
2017	False	True	6	3,975,873
2016	False	False	16	0
2015	True	False	12	0
2014	True	True	4	2,532,163
2013	False	False	16	0
2012	False	False	30	0
2011	True	True	2	4,005,971
2010	False	False	30	0
2009	False	False	30	1,751,722
2008	False	False	16	2,174,497
2007	False	False	12	1,132,595
2006	False	False	16	
2005	False	False	16	
2004	False	False	16	
2003	False	False	30	
2002	False	True	7	
2001	True	False	12	

Les 9 pires années (correspondant à une période de retour d'environ 3 ans, du rang 12 ou pire) sont 2001, 2002, 2007, 2011, 2014, 2015, 2017, 2019, et 2021. Avec les prévisions, on aurait déclenché pour 4 de ces 9 années, et jamais pour une année pas sur cette liste. Avec les observations, on aurait déclenché pour 5 des 9 pires années, et aussi jamais pour une année pas sur cette liste.

On voit aussi que les allocations les plus récentes de CERF se concordent bien avec les mauvaises années et les déclenchements.

[17] Tout le code d'analyse pour ce cadre est disponible publiquement en ligne sur GitHub à https://github.com/OCHA-DAP/ds-aa-mrt-drought

Déclencheur prévisionnel

Le tableau ci-dessous montre les déclenchements historiques du déclencheur prévisionnel. Les premiers quatre colonnes montrent où le seuil aurait été atteint dans un mois singulier d'émission des prévisions, tandis que les trois prochaines colonnes montrent quand le seuil aurait été atteint dans deux mois consécutifs, qui aurait déclenché le cadre.

	Fév.	*Mar.*	*Avr.*	*Mai*	*Fév./ Mar.*	*Mar./ Avr.*	*Avr./ Mai*	*Tout*
2025	False	False	False	False	False	False	False	False
2024	False	False	False	False	False	False	False	False
2023	False	True	False	False	False	False	False	False
2022	False	False	False	False	False	False	False	False
2021	False	False	False	False	False	False	False	False
2020	False	False	False	False	False	False	False	False
2019	False	False	False	False	False	False	False	False
2018	False	False	False	False	False	False	False	False
2017	True	False	False	False	False	False	False	False
2016	False	False	False	False	False	False	False	False
2015	True	False	True	True	False	False	True	True
2014	True	True	True	True	True	True	True	True
2013	False	False	False	False	False	False	False	False
2012	False	False	False	False	False	False	False	False
2011	True	False	True	True	False	False	True	True
2010	False	False	False	False	False	False	False	False
2009	False	True	False	True	False	False	False	False
2008	False	False	False	False	False	False	False	False
2007	False	False	False	False	False	False	False	False
2006	True	False	False	False	False	False	False	False
2005	False	False	True	False	False	False	False	False
2004	False	False	False	False	False	False	False	False
2003	False	False	False	False	False	False	False	False
2002	False	True	False	True	False	False	False	False
2001	True	True	True	True	True	True	True	True

Déclencheur observationnel

Le tableau ci-dessous montre les déclenchements historiques du déclencheur observationnel.

year	*Juil. 1*	*2*	*3*	*Août 1*	*2*	*3*	***Cumul. saison JAS***
2025	False	False	False	False	False	False	False
2024	False	False	False	False	False	False	False
2023	False	False	False	False	False	False	False
2022	False	False	False	False	False	False	False
2021	False	False	False	False	False	False	False
2020	False	False	False	False	False	False	False
2019	False	True	True	True	True	True	True
2018	False	False	False	False	False	False	False
2017	False	False	True	True	True	False	True
2016	False	False	False	False	False	False	False
2015	False	False	False	False	False	False	False
2014	False	False	True	True	False	False	True
2013	False	False	False	False	False	False	False
2012	False	False	False	False	False	False	False
2011	False	False	True	True	False	False	True
2010	False	False	False	False	False	False	False
2009	False	False	False	False	False	False	False
2008	False	False	False	False	False	False	False
2007	False	False	False	False	False	False	False
2006	False	False	False	False	False	False	False
2005	False	False	False	False	False	False	False
2004	False	False	False	False	False	False	False
2003	False	False	False	False	False	False	False
2002	False	True	True	True	True	True	True
2001	False	False	False	False	False	False	False

La dernière colonne (« Cumul. Saison JAS ») montre les 5 pires années basé sur les précipitations totales sur juillet-août-septembre. On voit qu'avec le déclencheur observationnel, on peut déclencher assez tôt dans la saison avec les précipitations totales jusqu'à la décade actuelle. Le graphique ci-dessous montre l'évolution des précipitations cumulatives à travers la saison.

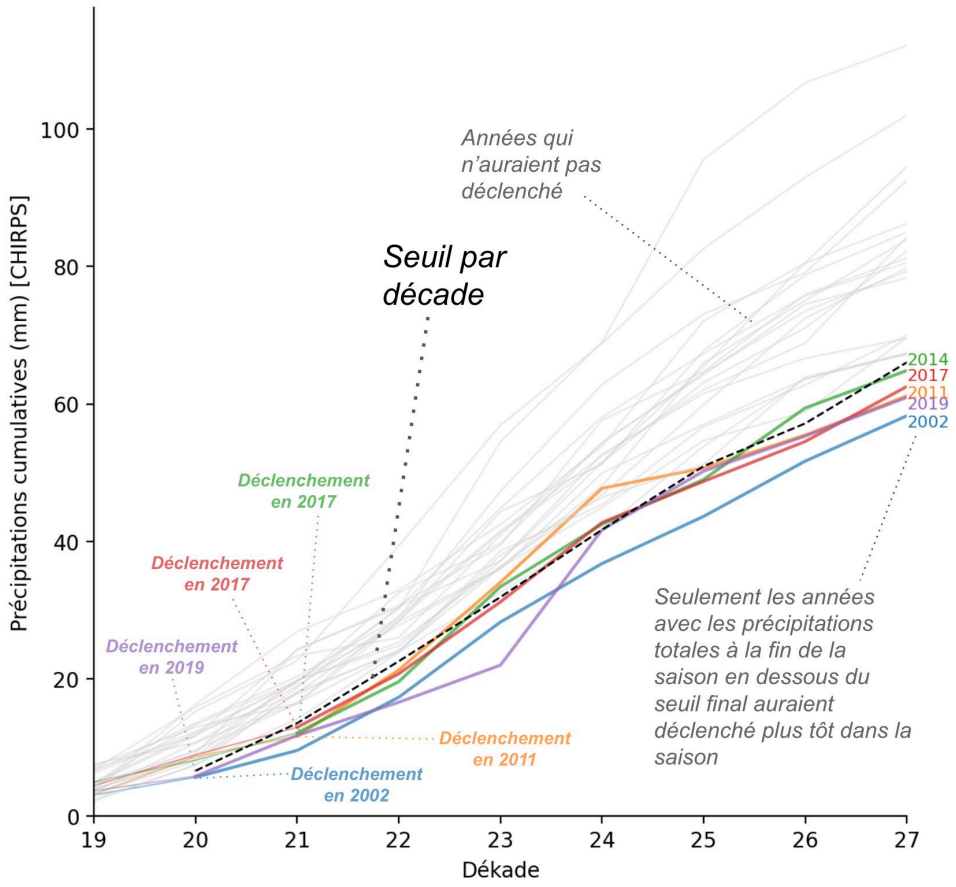

Il est à noter que toutes les décades de juillet-août-septembre sont affichées sur le graphique, tandis qu'on utilise seulement les décades du 2ième décade de juillet (décade 20) au 3ième décade d'août (décade 24) pour déclencher.

On voit que seulement les années avec les précipitations totales à la fin de la saison en dessous du seuil fin de saison (c'est-à-dire pour les précipitations saisonnières JAS totales) auraient déclenché plus tôt dans la saison avec le seuil qui évolue par décade.

Annexe 2. Composition du Groupe de Travail Spécialisé chargé de l'Action Anticipatoire

Prénom	Nom	Organisation	Fonction	Email	Téléphone
Groupe GTSAA					
Ahmedou	DIALLO	Délégation Générale à la Sécurité Civile et à la Gestion des Crises/MIDEC	Directeur DPCS	ahmedoudiallo5@gmail.com	49540020
Mohamed	ISSELMOU	CSA	Coordinateur DCAN	icheikh.sidoumou@yahoo.fr	22494022
		Direction en charge de l'Agriculture			
		Direction des filières au ME			
Cheikh	SADE	Registre social		cheikhouldsada@gmail.com	37568615
		Observatoire à la Sécurité Alimentaire/CSA			
		Direction en charge de la Mère et de l'Enfant /MS			
		Office national de l'assainissement /MH			
Aida	CAMARA	ONM/PAM	Agro/météorolgue	aida.camara@wfp.org	48887417
El Moctar	MED	Ministère de l'Elevage	Responsable RSE	moktarsidoumou@gmail.com	47010201
Mohamed Lemine	SIDI	ONM	Directeur prévision météo	sidiloudey2@yahoo.fr	46466244
*Partenaires**					
Mohamed	HABIB	Croissant Rouge Mauritanien	Responsable AA	mohamedhabib8885@gmail.com	36388491
Bibata	SANKARA	PAM	Chargée de programme AA	bibata.sankara@wfp.org	48887429
Abdoulaye	NDAO	PAM	Risk Financing Officer	abdoulaye.ndao@wfp.org	
Mohamed Sidda	MATALLA	PAM	Chef de programme adjoint	Mohamedsidda.matalla@wfp.org	
Navel	THIAM	PAM	Chargé Vulnérabilté et Résilience	navel.thiam@wfp.org	48887481
Momme	DUCROS	OIM	Chargé de programme	mducros@iom.int	48881044
Ndiaye	KANE	OIM	Associé de programme	nkane@iom.int	48881006
Oumou	VOULLANY	OIM	Senior Information Management and SIG	ovoullani@iom.int	34221917
Souleymane	SIDIBE	FAO		Souleymane.Sidibe@fao.org	
Abdallahi	KANE	FAO	Spécialiste M&E	abdallahi.kane@fao.org	47138798
Thierno	SALL	FAO	Spécialiste Ressources naturelles, eau, irrigation	thierno.sall@fao.org	41849836
Adama	OUEDRAOGO	UNICEF	Chef de Programme Santé-Nutrition	adouedraogo@unicef.org	48883006
Cheikh	DEHAH	UNICEF	Nutrition Manager	cdehah@unicef.org	48883663
Mohamedou	MOCTAR DIA	UNICEF	Responsable WASH	modia@unicef.org	
Mohamed Yahya	BAH	UNICEF		mybah@unicef.org	
Aïcha	BOUSLAMA	BCR	PBF Portfolio Manager	aicha.bouslama@un.org	
Caroline	GARCIA	BCR	Chargée adaptation au changement climatique et réduction des inégalités	caroline.garcia1@un.org	48884919
Stephanie	LARSEN	OCHA ROWCA	Humanitarian Affairs Officer – Anticipatory Action	Stephanie.larsen@un.org	
Tristan	DOWNING	OCHA Centre for Humanitarian Data	Data Scientist	Tristan.downing@un.org	

**Les représentants du système des Nations Unies, des ONGs, du Mouvement de la Croix-Rouge et du Croissant Rouge, des OSC Nationales et des autres organismes internationaux ou régionaux concernés assistent aux travaux du Groupe de travail en qualité de membres observateurs.*